🚨 **O desafio crônico da drenagem nas cidades brasileiras agora tem uma solução inteligente e integrada!** 🚨

Profissionais de engenharia, geoprocessamento e gestores públicos conhecem bem a realidade das nossas cidades: projetos de infraestrutura urgentes muitas vezes esbarram na lentidão e na complexidade técnica. O vai e vem interminável entre planilhas de cálculo hidrológico e softwares de SIG costuma ser demorado e propenso a erros.

Para mudar esse cenário, apresento a suíte **Método Racional Pro**, um plugin para QGIS desenvolvido para simplificar e acelerar o dimensionamento de microdrenagem, centralizando todo o fluxo de trabalho em um único ambiente!

Confira como essa ferramenta transforma o dia a dia do projetista (acompanhe as imagens do post):

🌍 **1. Integração Direta de Dados Espaciais:** O fluxo começa definindo a área de estudo. O plugin extrai parâmetros altimétricos diretamente de um Modelo Digital de Terreno (MDT) (Imagem 1). Se você não tiver um, a suíte conta com um **Gerador de MDT** que cria o modelo a partir das curvas de nível do seu projeto (Imagem 10).

💧 **2. Análise de Impermeabilidade Descomplicada:** Determinar a impermeabilidade da bacia é crucial. O plugin oferece uma classificação visual rápida sobre imagens de satélite ou ortofotos, ajudando a definir com precisão o coeficiente de escoamento (C) (Imagem 2).

⏱️ **3. Hidrologia Adaptada à Sua Região:** O sistema calcula o Tempo de Concentração (Tc) comparando instantaneamente métodos consagrados como Kirpich, Giandotti e Ventura (Imagem 3). Além disso, o módulo IDF permite inserir e salvar os parâmetros de chuva locais (como os dados de Juiz de Fora, por exemplo), eliminando a digitação repetitiva em projetos futuros (Imagem 4).

труб **4. Dimensionamento e Verificações Automáticas:** Chegou a hora do cálculo! O plugin dimensiona a galeria e emite alertas automáticos sobre verificações técnicas essenciais, como velocidade do escoamento, lâmina d'água e o regime de escoamento através do Número de Froude, garantindo o atendimento às normas (Imagem 5).

🗺️ **5. Lançamento Rápido de Rede e Perfil Longitudinal:** Ferramentas complementares permitem traçar rapidamente a rede de drenagem, contando automaticamente os Poços de Visita (PVs) (Imagem 8). O sistema gera instantaneamente o perfil longitudinal da rede, auxiliando o projetista na decisão ágil do traçado (Imagem 9).

📄 **6. Memória de Cálculo Completa:** Com um clique, gere um relatório final padronizado com todas as memórias de cálculo, mapas e parâmetros utilizados, pronto para aprovação e arquivamento em prefeituras (Imagem 7).

💡 **Transparência Técnica:** É importante ressaltar que o Método Racional é estritamente recomendado para bacias de microdrenagem (geralmente até 50-100 hectares). Ele não substitui análises dinâmicas complexas (como o SWMM) para áreas extensas de macrodrenagem, mas é uma ferramenta poderosa de apoio à decisão para a grande maioria das demandas municipais (imagem 6).

O planejamento eficiente previne desastres, economiza recursos públicos e melhora a qualidade de vida urbana.

💬 **O que você achou dessa integração entre Hidrologia e QGIS? Como isso otimizaria os projetos na sua cidade? Deixe suas impressões nos comentários!** 👇

#QGIS #DrenagemUrbana #EngenhariaCivil #Geoprocessamento #Hidrologia #MetodoRacional #GestãoPública #Inovação #Infraestrutura #CidadesInteligentes

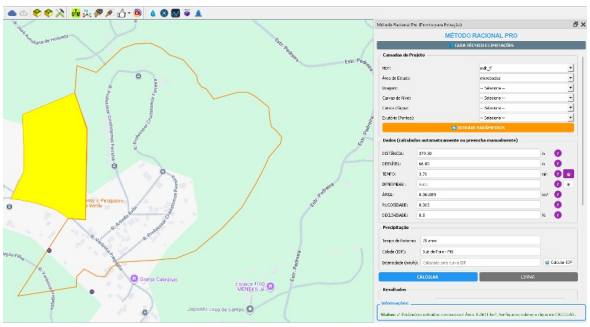

Imagem 1

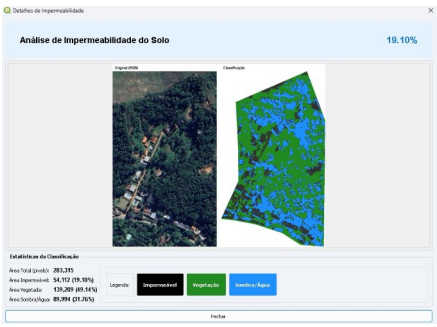

Imagem 2

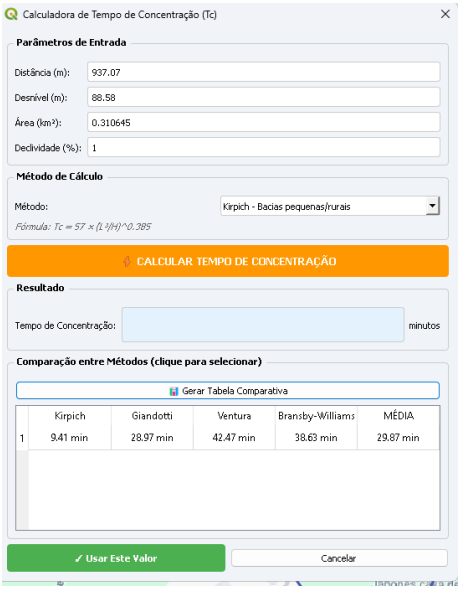

Imagem 3

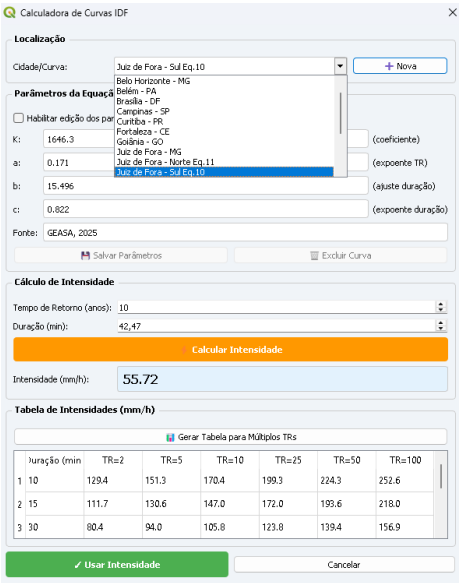

Imagem 4

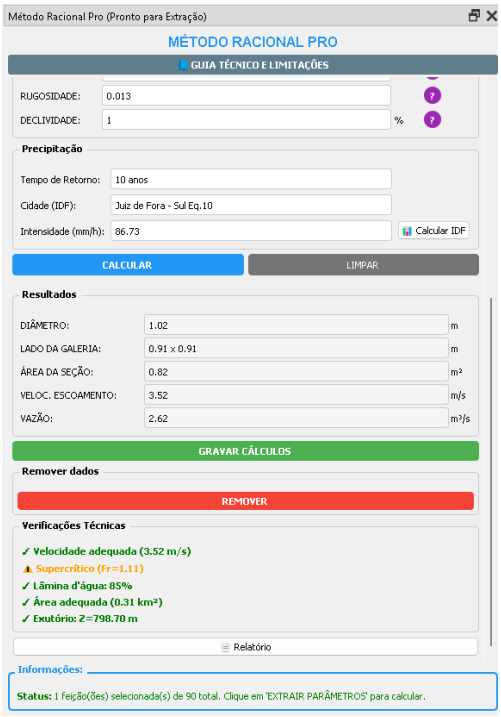

Imagem 5

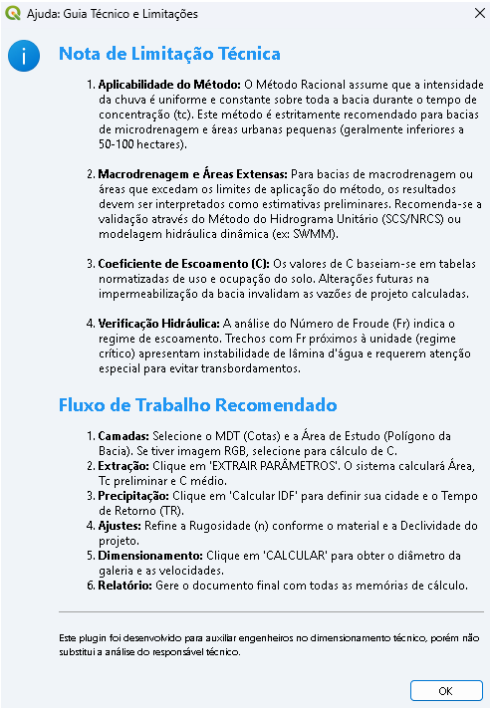

Imagem 6

Imagem 7

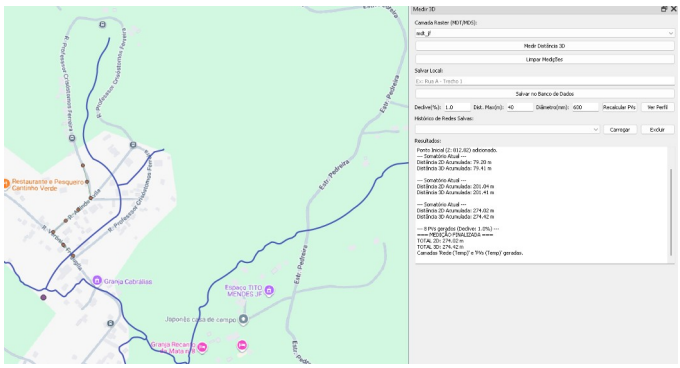

Imagem 8

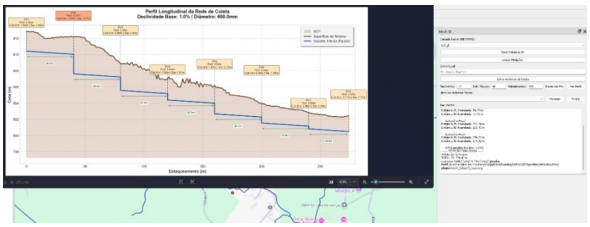

Imagem 9

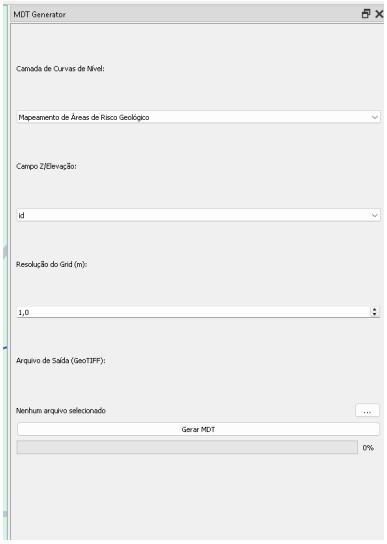

Imagem 10